Fiche réponse 2 ind B du 13/09/2024 (Ind A du 11/09/2024)

Paris 17-NCO-BNP-Affaire 090152 – Fiche réponse à l'avis SOCOTEC n°5 du 27/08/2024

Rédacteur : Julien PELSY

Édité le : 11/09/2024

Destinataires : MOE GEMO – SOCOTEC - LEGENDRE

Copie : Julien PELSY

Remarque N°2.100

2.100 | Définition des avoisinants *Cf rapport G2 PRO §4.3 :* *ZIG = en fonction de la longueur des tirants et avec un périmètre minimum d'environ 15 m autours des limites de la parcelle.* Références: 60004769-0.5-D. Plan d'implantation et coupes types de Paroi clouée 60004771-0.2-B. Plan d'implantation et coupes types de Paroi clouée 60005842-0.2-A. Plan élévations des parois	S	**Sur les différents plans d'élévations des parois, représenter l'ensemble des ouvrages avoisinants au sens de la NF P 94 500.** **Il y aura lieu d'indiquer clairement les ouvrages dans la ZIG, notamment si le métro est concerné, ainsi que la tranche 1 du projet, fondations bâtiment Rue Camille Blaisot etc..**	2

27/08/2024

SOCOTEC

Éléments examinés	Avis*	Observations et commentaires	N°
AVOISINANTS - Définition de la ZIG Références: 60005333-0.6-B. P17_T2_IN_EXE_FKI_FSP_I002_NDC_TZ_FD_270006_B-NDC Coupe E - Paroi berlinoise inversée 60004684-0.2-A. P17_T2_IN_EXE_FKI_FSP_I002_NDC_TZ_FD_270005_A-NDC Coupes G1 et G2 - Paroi clouée 60003634-0.4-B. P17_T2_IN_EXE_FKI_FSP_I002_NDC_TZ_FD_270000_B-NDC Coupe B-Avenue St ouen 60004672-0.2-A. P17_T2_IN_EXE_FKI_FSP_I002_NDC_TZ_FD_270004_A-NDC Coupe F-Paroi clouée-Rue Camille Blaisot 60003633-0.4-B. P17_T2_IN_EXE_FKI_FSP_I002_NDC_TZ_FD_270003_B-NDC Coupe D-Paroi Lutétienne 60003632-0.5-B. P17_T2_IN_EXE_FKI_FSP_I002_NDC_TZ_FD_270002_B-NDC Coupe C- Paroi berlinoise inversée 60003631-0.4-B. P17_T2_IN_EXE_FKI_FSP_I002_NDC_TZ_FD_270001_B-NDC Coupe A-Paroi clouée-Rue Camille Blaisot	S	**Le rapport G2-PRO version A, §4.3 indique que la ZIG sera en fonction de la longueur des tirants, et avec un périmètre de 15m minimum autour des limites de la parcelle. Cette valeur minimale inclut la bâtiment Rue Camille Blaisot.** **Pour le métro, il nous a été indiqué que sa position est à environ 22/24m de la parcelle, il conviendra donc d'évaluer l'impact sur la voute du métro en fonction de la position et la profondeur des tirants.** **De manière générale, il conviendra d'évaluer la cuvette de tassement du projet, et de décrire explicitement la ZIG du projet en tenant compte des différentes couches de sols présentes. Par la suite, une note justifiant la compatibilité des travaux avec le système des fondations avoisinants devra nous être transmise.**	516
		La variante du produit de cuvelage	

Réponse L'ouvrage métro ainsi que le l'ouvrage bâtiment rue Camille Blaisot sont hors influence des ouvrages de fondations spéciales. Nous joignons les annexes explicatives ci-après.

Les ouvrages de tirants sont suffisamment profonds pour ne pas être en influence avec les ouvrages mitoyens cités.

Ci-joint un retour pour le tassement du bâtiment avoisinant côté Rue Camille Blaisot :

Le bâtiment se trouve plutôt à 17.50m du nu extérieur du voile du soutènement :

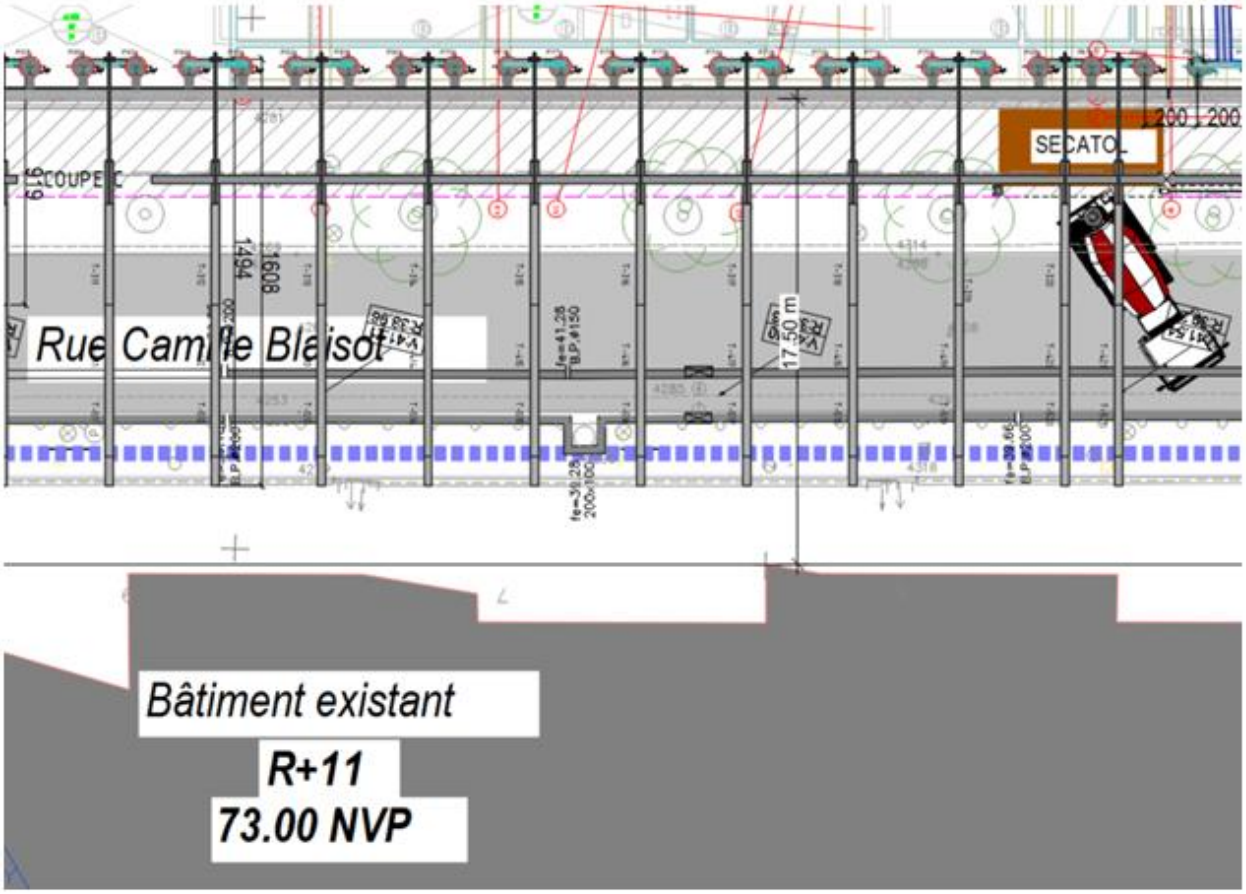

L'emprise du Coin de poussée du sol est de 11.30m et n'a pas donc d'influence sur le bâtiment existant.

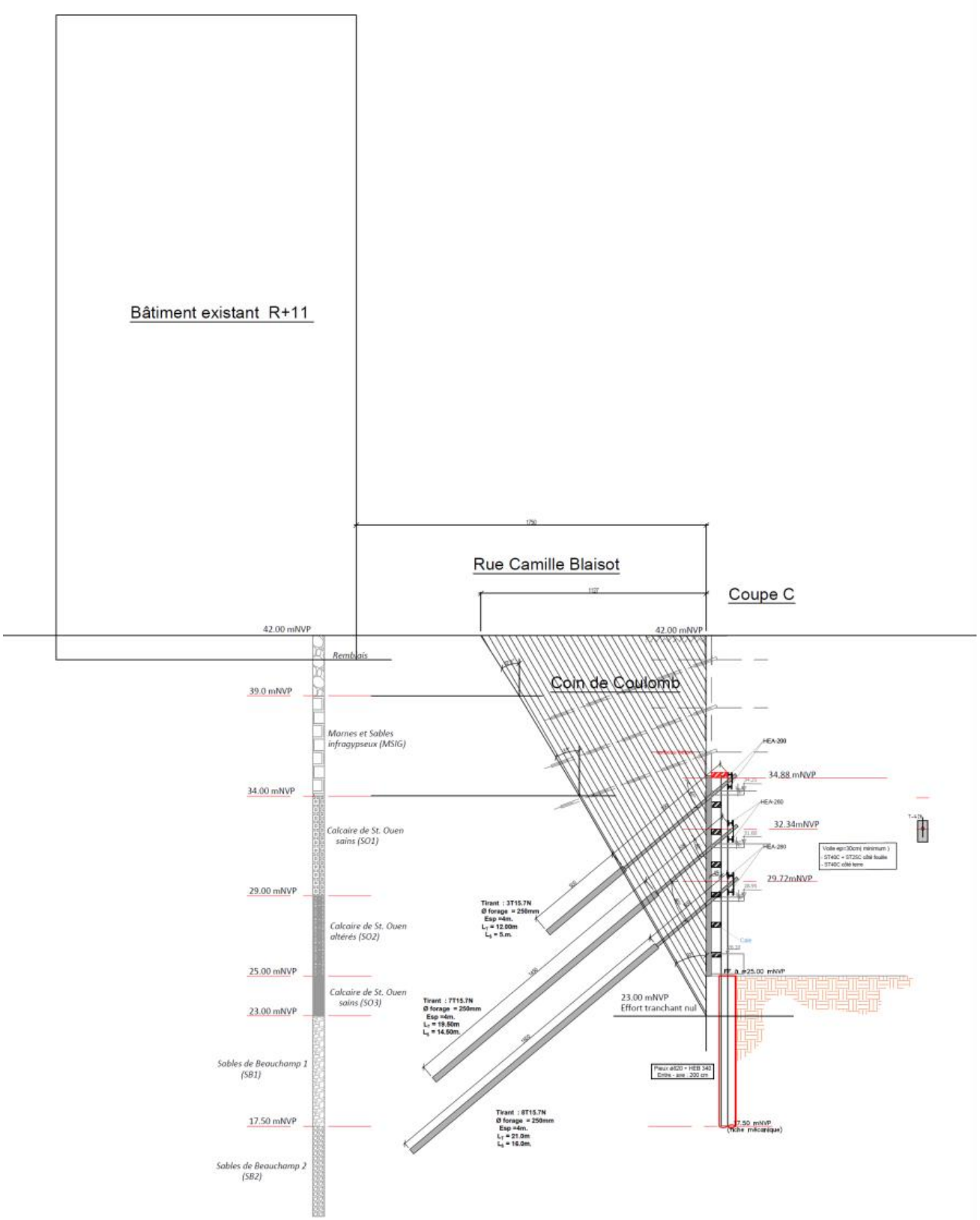

Les cercles de glissement présentés dans la note de calcul « P17_T2_IN_EXE_FKI_FSP_I002_NDC_TZ_FD_270002_B- NDC Coupe C- Paroi berlinoise inversée » (pages 68 et 70) s'arrêtent également entre 11.5m et 16m de distance du soutènement.

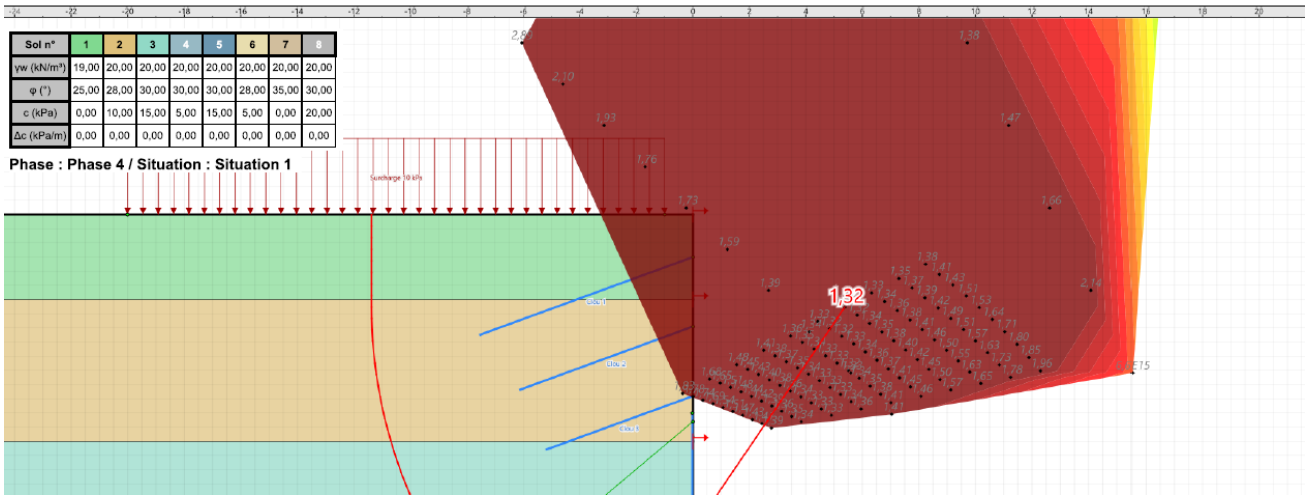

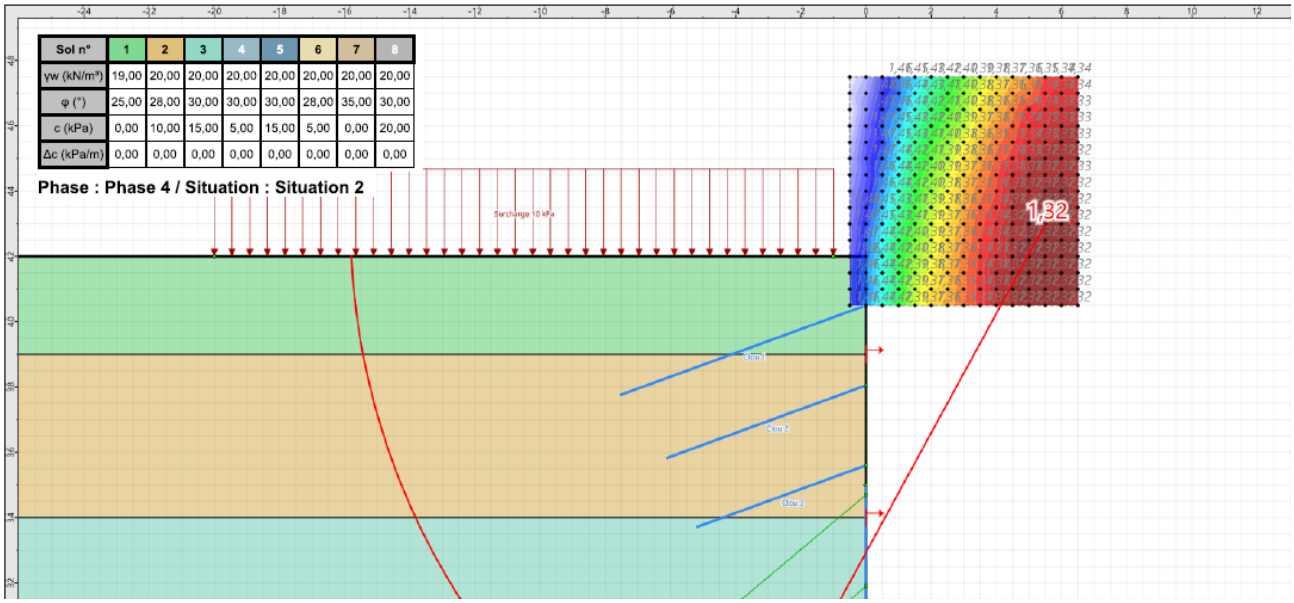

Nous retenons que un calcul plaxis n'est pas nécessaire pour vérifier le tassement de l'avoisinant.

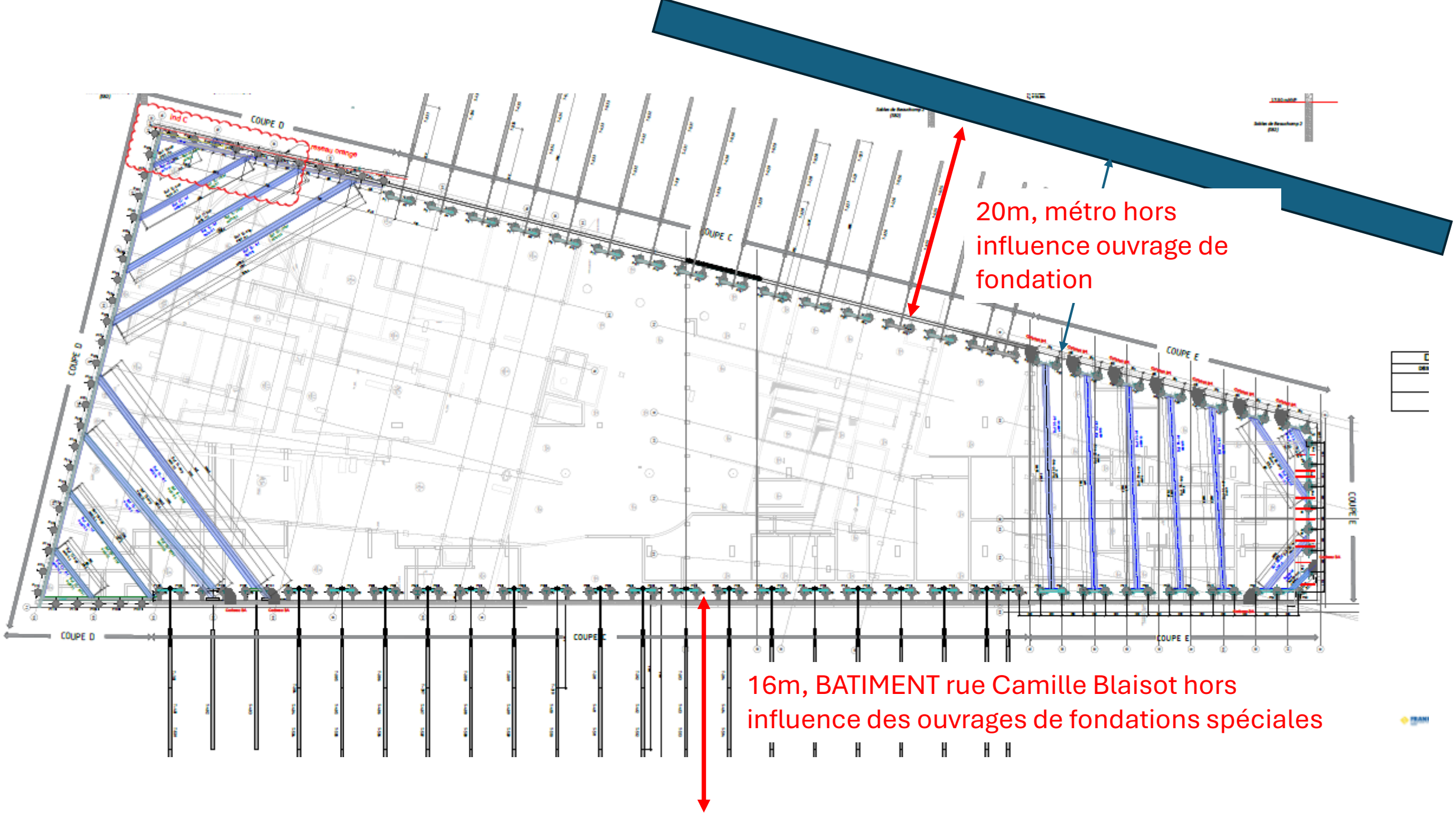
COUPE D
COUPE C
COUPE E
20m, métro hors influence ouvrage de fondation
16m, BATIMENT rue Camille Blaisot hors influence des ouvrages de fondations spéciales

DICT/DT METRO / RATP, avec localisation et niveau du tunnel

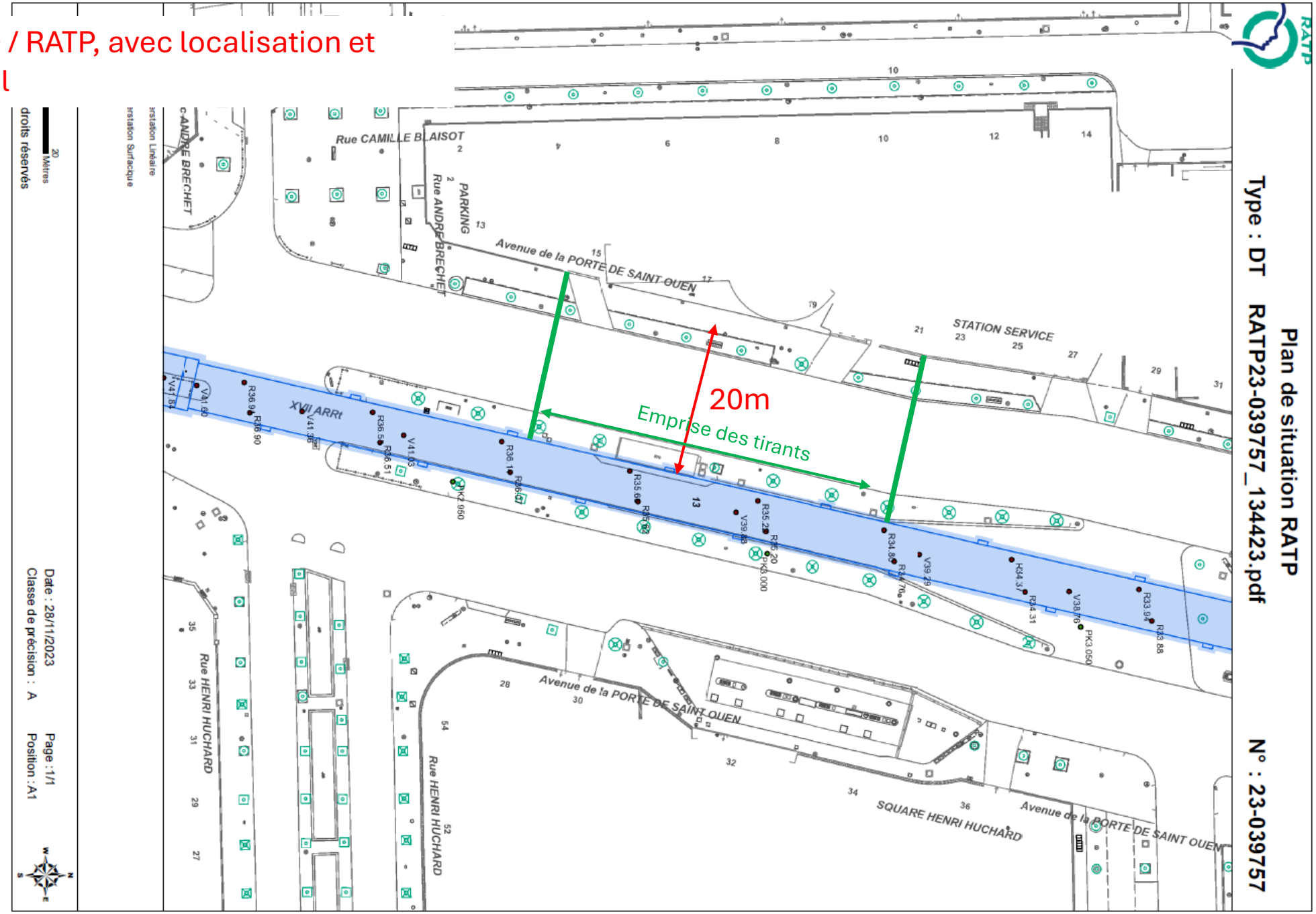

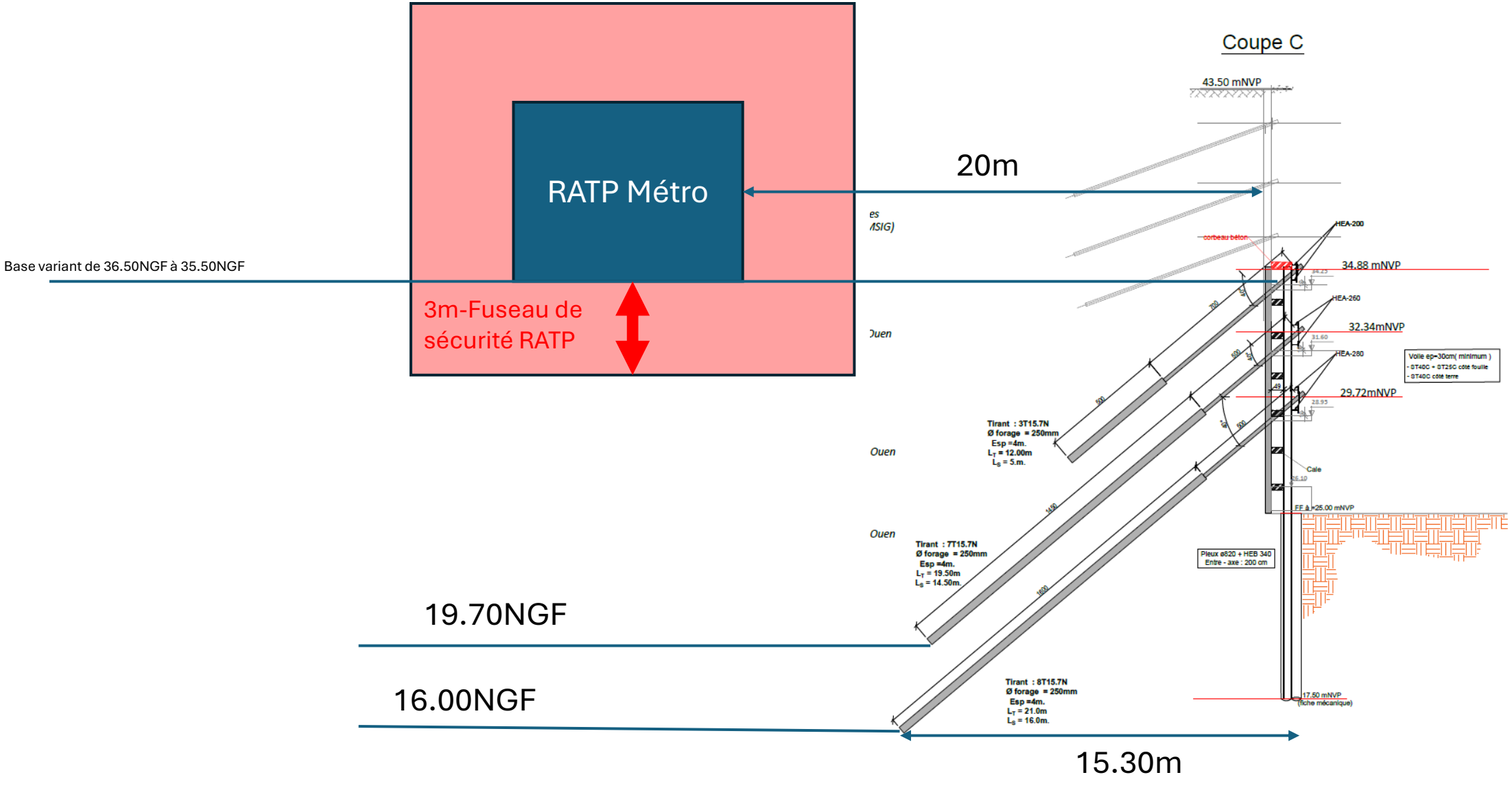

Tirants Hors emprise du fuseau de sécurité RATP coté Avenue de St Ouen